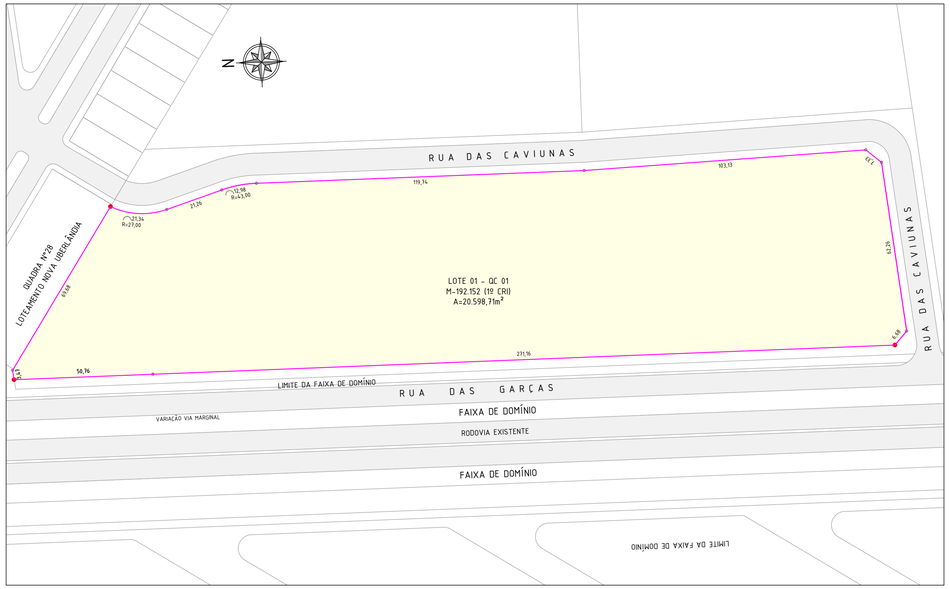

PLANTA DE
SITUAÇÃO CONFORME MATRÍCULA
ESC 1:1000

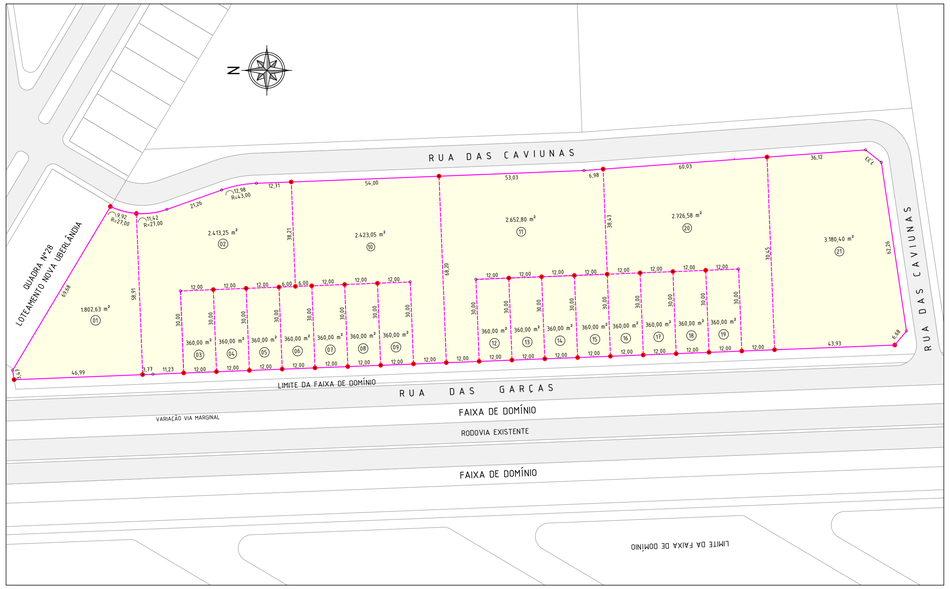

PLANTA DE
SITUAÇÃO PRETENDIDA
ESC 1:1000

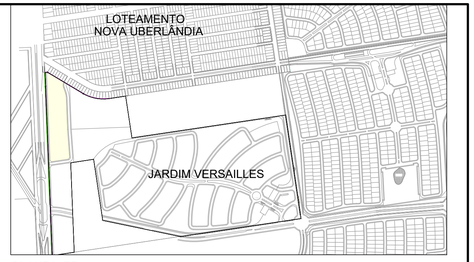

PLANTA DE
SITUAÇÃO
SEM ESC

Quadra - QC 01	
Lote	Área
01	1.802,63 m²
02	2.413,25 m²
03	360,00 m²
04	360,00 m²
05	360,00 m²
06	360,00 m²
07	360,00 m²
08	360,00 m²
09	360,00 m²
10	2.423,05 m²
11	2.652,80 m²
12	360,00 m²
13	360,00 m²
14	360,00 m²
15	360,00 m²
16	360,00 m²
17	360,00 m²
18	360,00 m²
19	360,00 m²
20	2.726,58 m²
21	3.180,40 m²
TOTAL:	20.598,71 m²

PLANTA DE
SITUAÇÃO FUTURA
ESC 1:1000

LEGENDA:

- ASFALTO
- MATRÍCULA (SITUAÇÃO ATUAL)
- MATRÍCULA (SITUAÇÃO PRETENDIDA)
- MATRÍCULA (SITUAÇÃO FUTURA)
- MARCO DE DIVISA DE CONFRONTANTE
- MARCO PERÍMETRO

PREFEITURA/DMAE

DATA	REVISÃO	ALTERAÇÃO
10/10/2025	00	EMISSÃO INICIAL
18/01/2025	01	ADEQUAÇÕES PMU
08/04/2024	02	DEVOLUTIVA CARTÓRIO
10/10/2025	03	ALTERAÇÕES DE DIVISAS

OBSERVAÇÕES:

TÍTULO:
PROJETO DE DESDOBRO DE LOTES

DATA:
10/10/2025

LOCAL:
LOTE COMERCIAL Nº1 (EXTERNO) DA QUADRA QC 01, DO LOTEAMENTO CONVENCIONAL E FECHADO JARDIM VERSAILLES - BAIRRO NOVA UBERLÂNDIA

CIDADE:
UBERLÂNDIA - MG

PROPRIETÁRIO:
CIDADE JARDIM - SPE PARCERIA IMOBILIÁRIA LTDA

ESCALA:
1:1000

OBJETIVO:
DESDOBRO

FOLHA:
ÚNICA

CONTEÚDO:
PLANTA COM ESQUEMA DE SITUAÇÃO CONFORME MATRÍCULA, PRETENDIDA E SITUAÇÃO FUTURA.

RS ENGENHARIA
INFRAESTRUTURA URBANA
DIRETOR COMERCIAL
SILVIO SIMÕES
CREA-MG 32238/D
(34) 9 8428.2140
DIRETOR TÉCNICO
TULIO RIBEIRO
CREA-MG 207690/D
(34) 9 8878.6801
topografia@ribeirosimoseseng.com
ribeirosimoesengenharia.com

ASSINATURAS:

CIDADE JARDIM - SPE PARCERIA IMOBILIÁRIA LTDA
15.522.298/0001-77

gov.br Documento assinado digitalmente
TULIO RIBEIRO DE QUEIROZ
Data: 10/10/2025 12:19:46-0300
Verifique em https://validar.iti.gov.br

TULIO RIBEIRO DE QUEIROZ
CREA-MG 207.690/D

ÁREA:
SIT. COF. MAT. (ATUAL) =20.598,71m²
SIT. FUTURA = VER QUADRO DE ÁREAS

DESENHO:
ANA CAROLINA B.

ARQUIVO BASE:
DES_QUADRA.C1 - Lotes com Verticalização Rev23.09.25.dwg

REVISÃO:
03

175_DES_QUADRA.C1_10.10.25_R3.DWG